《伪满皇宫历史文化街区保护规划（2023–2035 年）》

（公示稿）

一、总则

1.编制目的

为落实国家关于加强历史文化保护传承的要求，促进城市建设与经济、文化、环境的协调发展，保护伪满皇宫历史文化街区丰富的历史文化遗产及其历史环境，延续街区传统格局和风貌，承载民族与地方特殊的历史记忆，实现历史文化街区的科学保护与永续利用，结合街区实际情况，制定本规划。

2.适用范围

本规划是伪满皇宫历史文化街区保护和发展的法定文件。历史文化街区规划范围内制定的相关建设规划及设计方案，开展的各项保护与建设活动，应当符合本规划的要求。

3.规划范围

伪满皇宫历史文化街区位于长春市宽城区，其范围东至长图铁路，南至光复路，西至兴起胡同，北至长利路、东八条街、长白路、永宁路。规划总用地面积约为 25.05 公顷。

4.规划期限

本次规划期限为 2023-2035 年。

近期：2023-2025 年；远期：2026-2035 年。

二、历史文化价值和特色

1.街区特色

伪满皇宫是清朝末代皇帝爱新觉罗·溥仪在日本扶植下，充当“伪满洲国”

征求意见稿

傀儡皇帝时的宫廷旧址。部分主体建筑始建于 1913 年，兴建于 1932 年，1945 年扩建为现状规模。历史上的伪满皇宫既有中国传统建筑，又有欧陆风情的楼宇，皇宫内的建筑中外并置，是当时中国东北特殊社会状况在建筑上的真实反映。

（1）空间特色——院落空间紧凑有序，功能分区明确。伪满皇宫博物院院墙范围内的四大区域格局清晰、分区明确，分别为中部宫廷游览区、西部休闲文化区、东部警示教育区和南部文化创意区。各个区域通过伪满皇宫现存院门、院墙和绿化分隔开来，基本保持延续了原有的规模和边界。中部宫廷游览区完整延续了原有外廷、内廷东院和内廷西院三个分区。整体空间形态既有轴线布局的手法，又有内外、动静等功能分区的理念，形成了前庭后寝、穿宅过院、曲径通幽、回廊相连的紧凑而有序的院落空间。

（2）建筑特色——形式丰富，中外并置。伪满皇宫从 20 世纪初缉熙楼等建筑的落成，到 21 世纪东北沦陷史陈列馆、博物馆之眼艺术宫的相继竣工，共经历了百年的时间。在不同时期，不同背景下先后建成的建筑，逐步形成了今天的格局，成为伪满皇宫建设历程的见证。

（3）环境特色——兼有中国传统皇家御苑和日式园林等多种风格。伪满皇宫的东御花园是由日本园林师佐藤昌设计并监造的具有日本园林风格的花园，园内假山、人工瀑布、小溪、养鱼池、花坛、草坪以及栽种的各种树木连成一体，动静相衬，步移景异。西御花园内栽植有多种花草树木，此外还有凉亭、假山、小桥和池水，整个花园小巧玲珑，具有中式园林的秀美之风。

2. 历史价值

伪满皇宫是日本侵华战争不可辩驳的也是最为重要的实物罪证，具有极其重要的现实意义与历史价值。

伪满皇宫内的建筑和花园展现了长春近代建筑发展在审美上的多元化趋势和东西建筑文化的融合，具有较高的艺术价值。

伪满皇宫的建筑采用了当时的比较先进的理念，在结构、工艺及材料上，代表了当时日本近代建筑技术水平及我国近代建筑施工水平，具有很高的科学价值。

伪满皇宫是极为重要的爱国主义教育示范基地和抗日战争纪念地，具有重要

征求意见稿

的社会文化价值。

三、目标原则与保护对象

1.规划目标

全面挖掘和梳理伪满皇宫的价值，在完整、原真的保护伪满皇宫历史文化街区内院落空间、文物建筑、环境景观等基础上，多样化发掘其使用功能，充分发挥伪满皇宫作为警示性爱国主义教育基地的重要作用。

2.保护原则

（1）历史原真的原则

对伪满皇宫内的文物保护单位进行严格保护和修缮，进行修缮处理时，新增部件应能区别于原建筑物，不能混淆、以新仿旧。复建的建筑和恢复的环境应查找史料尽可能恢复其原本的风貌特色。

（2）整体保护的原则

在保护活动中，除了对文物保护建筑实施保护外，还应对承载历史信息的各种要素，包括碉堡、防空洞、游泳池、园林景观、古树名木、遗址遗迹等进行保护。在历史文化要素的保护上，应对中国近代历史资料进行挖掘，整理文字记载和口述文化遗存，全面记录伪满皇宫特殊的历史记忆。

（3）保护与利用相结合的原则

伪满皇宫是我国至今保存较完整的宫廷特色遗址之一，本次保护规划中突出保护伪满皇宫内精致的建筑艺术，挖掘其所经历的特殊历史事件，在使用中结合其警示功能，彰显伪满皇宫的警示作用和教育意义。

3.保护对象

本街区的保护对象主要包括传统街巷、历史院落空间、建筑、历史环境要素及历史文化要素。

保护对象分类	具体对象
传统街巷	长利路、东九条街、光复路、东八条、长白路

征求意见稿

保护对象分类		具体对象
历史院落空间		伪满皇宫院墙围合而成的西部区、核心区、东部区与南部区的院落空间环境
建筑	文物保护建筑	同德殿、书画楼、面点间、缉熙楼以及东南西厢房、中和门、勤民楼、日本宪兵室、嘉乐殿、怀远楼、宫内府（正房、东西厢房）、畅春轩、植秀轩、卤簿车库、近卫军营房等 25 栋建筑
	传统风貌建筑	花窖、马厩、禁卫军营房等 11 栋建筑
历史环境要素	构筑物	游泳池、御用防空洞、天照大神防空洞、院墙、门 8 座、碉堡 11 座
	遗址	建国神庙遗址
	园林景观	东御花园（养鱼池）、西御花园、假山
历史文化要素		伪满皇宫街区范围内的历史事件等

四、保护范围及保护控制措施

1.历史文化街区保护区划

伪满皇宫历史文化街区保护范围包括核心保护范围和建设控制地带，总面积 25.05 公顷。

核心保护范围为街区内文物保护单位相对集中的区域，规划将现状伪满皇宫博物院的范围确定为核心保护区范围，用地面积 13.55 公顷，占本历史文化街区总面积的 54.09%。

建设控制地带为街区以内、核心保护区以外的区域，用地面积 11.50 公顷，占本历史文化街区总面积的 45.91%。

2.核心保护范围保护控制要求

（1）建设活动管控要求

严格保护核心保护范围内的传统街巷、历史院落空间格局特征，保护文物保护建筑的高度、体量、材质、色彩、形式和空间布局，保护和恢复街区的整体历史风貌。

除必要的基础设施和公共服务设施外，不得进行新建、扩建活动；不得新建

征求意见稿

有环境污染的设施；严禁私自拆除、改造和翻建文物建筑、传统风貌建筑。

进行新建、改建、扩建时应提取文物保护建筑的典型符号和核心元素进行设计，确保在体量、色彩、材质等方面与文物保护建筑的历史风貌协调，建设活动不得破坏传统格局和历史风貌。

为平衡核心保护范围内传统风貌保护和生产生活需要，允许进行一定程度的地下空间开发，但不得对地上保护建筑造成破坏。

（2）土地利用管控要求

严格控制伪满皇宫博物院文化展览功能。

核心保护范围内不设置绿化控制线，新建、改建、扩建建筑控制线应与相邻保护建筑控制线保持一致。

核心保护范围内新建、改建、扩建的建筑间距应当符合历史肌理和尺度，并满足现行日照、消防、卫生安全标准和管线敷设所需间距，无法满足的，其间距不得小于原有建筑间距。

（3）环境景观管控要求

与历史环境相冲突的环境要素应进行整治，环境整治工作不得破坏本街区的历史风貌。

历史环境要素的恢复，应在高度、体量、材质、色彩、形式等方面按历史原貌恢复，新增设的绿化、铺装、街道家具、灯光照明等环境要素不得破坏本街区的建筑空间环境和历史景观环境。

严格管控户外广告和牌匾标识，不得遮挡、覆盖具有历史风貌特色的建筑立面，不得破坏建筑空间环境和景观。

3.建设控制地带保护控制要求

（1）建设活动管控要求

建设控制地带内允许进行新建、改建和扩建活动，但不得影响整体空间格局，并应当在使用性质、高度、体量、材质、色彩、形式等方面应与文物保护单位及周边环境相协调。

建设控制地带内新建、扩建和改建道路和街巷时，应与传统街巷的尺度、走

征求意见稿

向协调。

建设控制地带内允许进行地下空间开发，但不得对保护建筑造成破坏。

对质量差的建筑和质量虽好但严重影响历史风貌且难以改善的建筑应逐步拆除，拆除建筑后以重建、复原传统风貌建筑为主。

（2）土地利用管控要求

建设控制地带内功能宜为文化、展览、居住、小型旅游商业等，不得引入工业、仓储、大型公用设施、学校、医疗卫生、大型商业、金融办公等可能造成污染、具有安全隐患、建筑体量过大、破坏肃穆氛围的功能。

建设控制地带内不设置绿化控制线，新建、改建、扩建建筑依据传统街巷原空间尺度进行退让，形成界面连续的街道空间。

建设控制地带内新建、改建建筑的间距应当符合历史肌理和尺度，并尽量满足现行日照、消防、卫生安全标准和管线敷设所需间距，无法满足的，其间距不得小于原有建筑间距。

（3）环境景观管控要求

严格管控户外广告、牌匾标识、灯光等环境要素，不得破坏街区建筑空间环境和景观。

五、分类保护与整治措施

1.传统街巷保护与控制要求

严格保护二类传统街巷长利路的名称及走向，严格控制街巷空间尺度，禁止拓宽街巷宽度，对沿街建筑进行分类整治，新建建筑的高度、体量、色彩、风格等方面应与传统风貌相协调。

保护三类传统街巷东八条街、长白路、东九条街、光复路的名称、走向不变。控制沿街新建、改建、扩建建筑的高度、体量、色彩、材质、风格；对沿街影响历史风貌的建（构）筑物进行整治。

整治传统街巷环境，拆除沿街私搭乱建建筑，保护历史环境要素，统一布置路灯、指示牌、垃圾箱等与街区风貌相协调的街道家具和环境小品。

征求意见稿

改善街巷的基础设施条件，对占用街巷空间且与传统风貌不协调的电线杆、变压器、架空电线等市政设施进行改线或入地改造。

发掘街巷故事，设置标识牌展示相关历史信息。

2.历史院落空间保护与控制要求

本街区院落空间以围合式为主，应结合观览流线体现伪满皇宫紧凑有序，功能各异的院落空间。

“核心区”应保持伪满皇宫外廷、内廷东院和内廷西院的院落格局和边界，拆除加建建筑和杂物，恢复原有肌理。根据历史资料对外廷和内廷院落的铺装、绿化等进行复原，加强对古树名木的保护。

“西部区”为跑马场、花窖和御用车库，复建建筑质量好，虽然该区域与伪满皇宫的真实历史格局有差异，但恢复难度较大，应保持现状进行日常维护。在区域的重要节点如兴运门、保康门等处设置简介牌，标识出该区域原有历史风貌，展示历史资料。

“东部区”东北沦陷史陈列馆、博物馆之眼艺术馆是伪满皇宫博物院为了丰富文化展示和完善文物保存功能而新建的建筑，在院落空间的营造上应当结合建筑使用功能的要求，延续宜人尺度和围合式院落。

“南部区”为用作 M+文化创意街区的近卫军营区，保持其现有院落格局、铺地和绿化，定期维护，街区尺度保持现状。

3.建筑分级保护与整治要求

本着保护街区风貌和传统空间格局的要求，结合街区目前的实际状况，将街区内的建（构）筑物分为文物保护建筑、传统风貌建筑、与传统风貌相协调的建筑、与传统风貌不协调的建筑四类进行保护和整治。

（1）文物保护建筑

街区内文物保护单位共计 1 处，为国家级文物保护单位。其中包含 25 栋文物保护建筑（以文物主管部门公布为准）。

坚持不改变原状、最小干预原则，对已经完成修缮的同德殿、缉熙楼、勤民

征求意见稿

楼等文物保护建筑进行保养维护。保养应禁止任何改变建筑平面、立面、结构、装饰、技术及工艺等活动，可增加不影响所在地段功能、风貌、不影响建筑结构、内部环境的必要设施、设备或生活改善类构件、装饰物等，以及国家、省、市相关规定要求增设的其它不影响文物建筑风貌和保护要求的设施、设备；文物建筑轻微渗漏的，可进行简易防漏修缮，保持建筑原风貌。

坚持建筑保护价值和安全性优先，对面点间等文物保护建筑进行修缮。修缮设计方案应包含历史建筑价值特色、历史格局的说明，对建筑功能、平面布局和建筑结构的变更、对建筑价值特色和价值要素影响评估说明等内容。

修缮工作应延续文物建筑的原有功能结构，为适应时代需要可对建筑进行局部功能空间的调整。不得改变建筑的平面轮廓，但允许因建筑加固需要而采取的必要内部墙体和平面的调整行为。原则上不得改变建筑的外立面，确需调整的，应采取原工艺、原材料对建筑墙体进行择砌、挖补及裂缝灌注等低影响措施。原则上不得改变建筑屋面，全面评估历次维修痕迹的考证价值，不得依照建筑始建状态对现存屋面采取恢复“始建”建设；因安全需要，必须改动建筑屋面的情况，原则上应保持原屋面形式。原则上不得改变建筑层高，但依据评估结果，对建筑楼板采取加固或因建筑结构加固对层高略有影响的，或因建筑开放需要、价值评估结果支持的，可做局部调整，但不得改变建筑高度。原则上不得改变建筑的结构，建筑原结构不具有显著价值的，因保护需要而不得不调整的，可做局部调整替换。除评估结果需要改变或拆除的“不协调”装饰外，不得改变建筑内外具有保护价值的所有装饰。除必须对建筑增设不影响保护价值的节能、安保、消防等必要设施、设备外，原则上不得随意新增其他任何设施设备。

（2）传统风貌建筑

传统风貌建筑是指除文物保护单位、历史建筑之外，具有一定建成历史、对历史文化街区整体风貌的形成具有价值和意义的建筑物。街区内现存传统风貌建筑 11 栋。

街区内传统风貌建筑根据外观现存情况、功能使用情况、安全情况等方面采取改善的整治措施，重点从功能性质、平面、立面、结构、装饰、技术工艺等 6

征求意见稿

个方面规范和指引建筑整治行为。改善活动原则上可根据使用需要局部调整建筑平面轮廓和内部平面布局、优化建筑结构；不得改变建筑价值要素集中立面，因建筑安全和保护需要可对其它立面做局部调整；可以改变建筑层高；不得改变屋面形式；保护其保护价值集中立面的特色装饰，不得“拆旧用新”，可局部调整室内外装饰，不得破坏和影响原建筑保护价值要素；可改变建筑使用性质、内部部分功能、进行必要的地下功能建设；鼓励探索利用新型历史建筑保护技术、工艺；充分合理使用建筑原构件、材料。

（3）与传统风貌相协调的建筑

与传统风貌相协调建筑是指对历史文化街区整体风貌没有影响的建筑物。街区内与传统风貌相协调的建筑共计 23 栋。

开展保护整治活动应首先进行安全排查及评估，并委托具有相应专业工程设计资质的专业技术单位编制维修、改善设计方案。为满足使用和生活改善需求，与传统风貌相协调建筑保护整治工作允许调整优化建筑结构、平面布局、建筑高度、建筑层高、使用性质和内部部分功能，调整楼梯、门窗等构件，以及进行必要的地下功能建设。

（4）与传统风貌不协调的建筑

应对街区内棚户简屋、破坏街区历史格局和低密度空间的大体量建筑等与传统风貌不协调的建筑、构筑物进行整治。整治活动开展前应首先进行安全排查及评估。

坚持以人为本、安全节约的原则，针对已经建成、使用状况良好、且满足安全条件的建筑，在充分尊重民意和专家意见的基础上，采取必要的改建和修饰等保留整治措施，促进建筑与街区风貌的协调。

采取拆除重建措施的，原则上应采用与街区传统风貌建筑统一的样式；拟采用现代建筑形式的，应确保建筑与街区传统风貌协调。

采取拆除不建措施的，其原址应优先作为公共绿地、室外健身场所、小型广场等公共开放空间，提高街区的公共环境品质和设施水平。公共空间建设应与历史街区风貌协调，延续历史文脉。

征求意见稿

4.历史环境要素的保护与控制要求

街区内的文物保护单位，除包含25栋文物保护建筑外，还包含构筑物、遗址、园林景观等历史环境要素（以文物主管部门公布为准）。对街区内碉堡、院门、院墙、防空洞等进行日常维护，对街区内损坏较严重的构筑物进行现状整修，以恢复构筑物的历史原貌，重现街区历史风貌。保护伪满皇宫东西御花园的园林景观，在保持树木、水池、假山等中式、日式特色景观要素不变的基础上丰富绿化层次，增加景观立体性。

六、土地利用规划

1.用地规划

街区内建设用地总面积为25.05公顷，用地类型包括居住用地、公共管理与公共服务用地、交通运输用地、绿地与开敞空间用地。

2.用地指标控制

建筑高度：核心保护区范围内的高度控制，维持建筑原高度不变。依据历史资料进行风貌恢复时，恢复建筑和新建建筑高度不应高于街区内传统建筑的高度，同时应满足文物保护单位对周边建筑高度的要求。核心保护区内的薰南楼位于伪满皇宫博物院入口处，该建筑体量过大，高度较高，对街区内文保建筑的观赏产生了一定程度的遮挡，对街区内景观影响较大，远期要对该建筑进行降层处理，将该建筑高度控制在9米以下。建设控制地带内的高度控制，原则上维持现状建筑高度，新建或扩建的建筑高度控制在18米以下。根据实际建设情况，新建建筑高度可以在控高的基础上上下浮动20%，但应满足文物保护单位保护规划对其周边建筑高度的要求，以及城市视廊、街景、对景等对建筑高度的要求。

容积率：核心保护区范围内容积率维持现状，建设控制地带范围内改造地块的规划容积率小于等于1.4。

建筑密度：核心保护区范围内建筑密度维持现状，建设控制地带内改造地块的建筑密度不应大于28%。

征求意见稿

绿地率：街区内鼓励增加各类绿地，在满足街区使用功能、安全和疏散的前提下，利用各类开敞空间设置绿地。建设控制地带内改造地块的绿地率不应小于30%。

七、活化利用规划

1.业态引导

鼓励街区在以文化陈列展示为主要功能的基础上，引进多元业态，推动街区活力提升，但业态形式不得破坏伪满皇宫肃穆的文化氛围。

分类引导街区业态功能发展，合理控制街区置换功能，严格控制文物保护单位功能置换类型，继续保持展示陈列功能。核心保护区内应以文化展览为主，少量用于配套办公、服务和文化体验。建设控制地带内鼓励发展文化交流、学术研究、文化创意、文化休闲等相关文化业态以及社交餐饮、商业零售等配套服务。

2.展示规划

延续现有展示分区格局，以莱薰门前广场为中心，分别设置中部核心陈列展示、东部警示教育、和西部休闲体验三条游览路线，三条游线相互关联而又独立，满足不同人群游览需求。

中部核心陈列展示游线：依托文保单位建筑群和周边环境要素，按照院落功能格局和边界合理安排游线，通过场景复原和展示讲解比较真实地反映出文物建筑原有的历史功能，直观深刻的展现“伪满洲国”的傀儡性质和溥仪的真实处境。

东部警示教育游线：北侧以东北沦陷史陈列馆为载体，全面反映东北十四年沦陷史，展示东北人民艰苦卓绝的抗战精神。南部以文化创意、艺术展览为主题，依托近卫军营房打造的M+文化创意街区和博物馆之眼艺术宫共同展现街区复合、多元的特色文化。

西部休闲体验游线：以传统展示、文化体验为特色，在兴运门以西区域，用环形游线串联起卤簿车库、百年机车馆、御用花窖、跑马场、禁卫军营房、皇宫剧场等节点，打造休闲体验游线。

征求意见稿

伪满皇宫历史文化街区保护规划（2023-2035年）

PROTECTION PLANNING OF HISTORICAL AND CULTURAL DISTRICT OF MANCHUKUO IMPERIAL PALACE

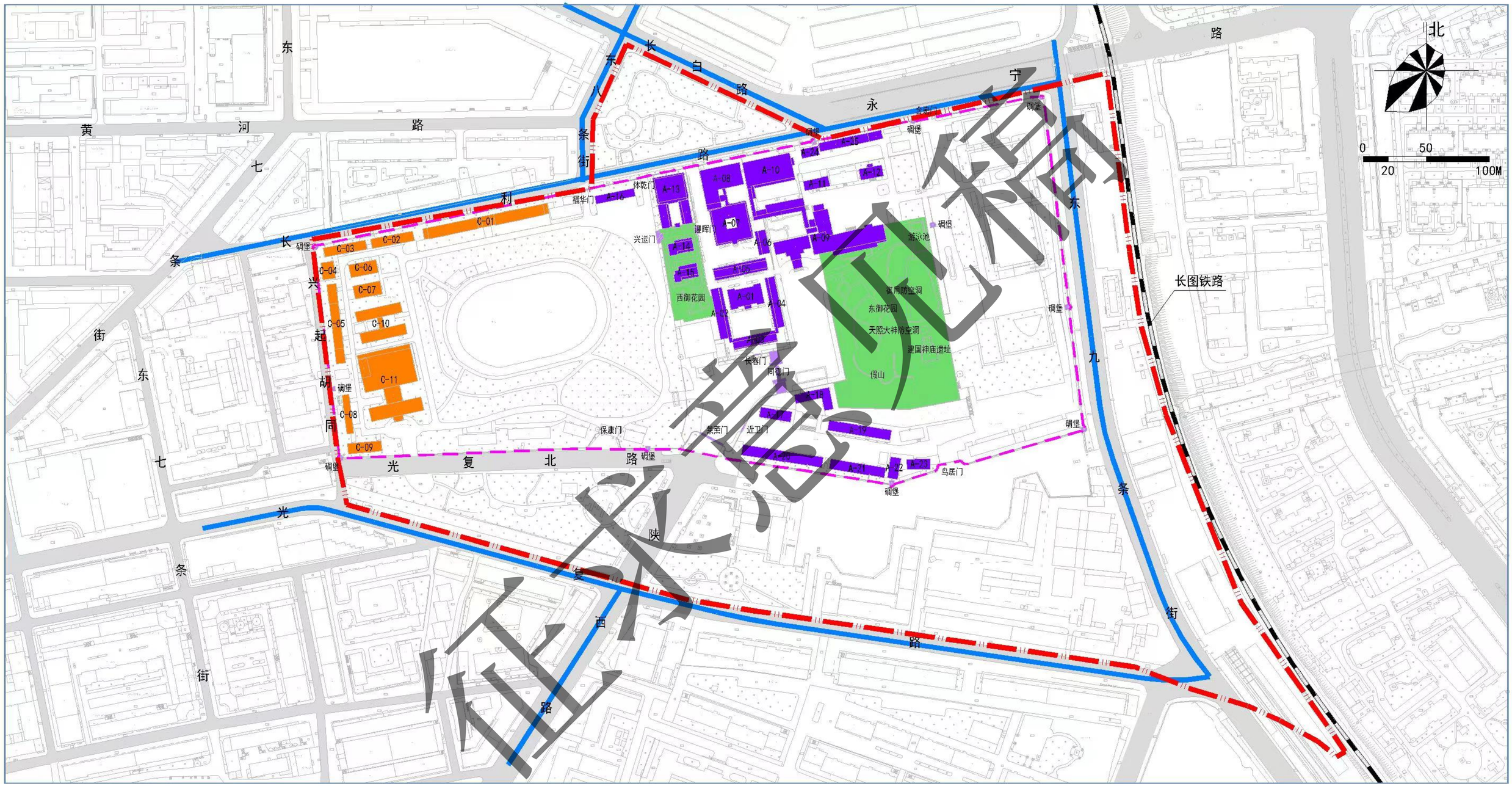

征求意见稿

图例

- 历史文化街区界线
- 核心保护区界线
- 现状道路
- 文物保护单位（建筑）
- 文物保护单位（构筑物）
- 文物保护单位（遗址）
- 文物保护单位（园林景观）
- 传统风貌建筑
- X-XX 建筑编号
- 传统街巷

注：文物保护单位以文物主管部门公布为准

03 历史资源分布图

DISTRIBUTION MAP OF HISTORICAL RESOURCES

伪满皇宫历史文化街区保护规划（2023-2035年）

PROTECTION PLANNING OF HISTORICAL AND CULTURAL DISTRICT OF MANCHUKUO IMPERIAL PALACE

征求意见稿

图例

- 历史文化街区界线
- 核心保护区界线
- 现状道路
- 文物保护单位（建筑）
- 文物保护单位（构筑物）
- 文物保护单位（遗址）
- 文物保护单位（园林景观）
- 文物保护单位保护范围界线
- 文物保护单位建设控制地带范围线
- 核心保护区
- 建设控制地带

05 保护区划图

PROTECTION ZONING MAP

伪满皇宫历史文化街区保护规划（2023-2035年）

PROTECTION PLANNING OF HISTORICAL AND CULTURAL DISTRICT OF MANCHUKUO IMPERIAL PALACE

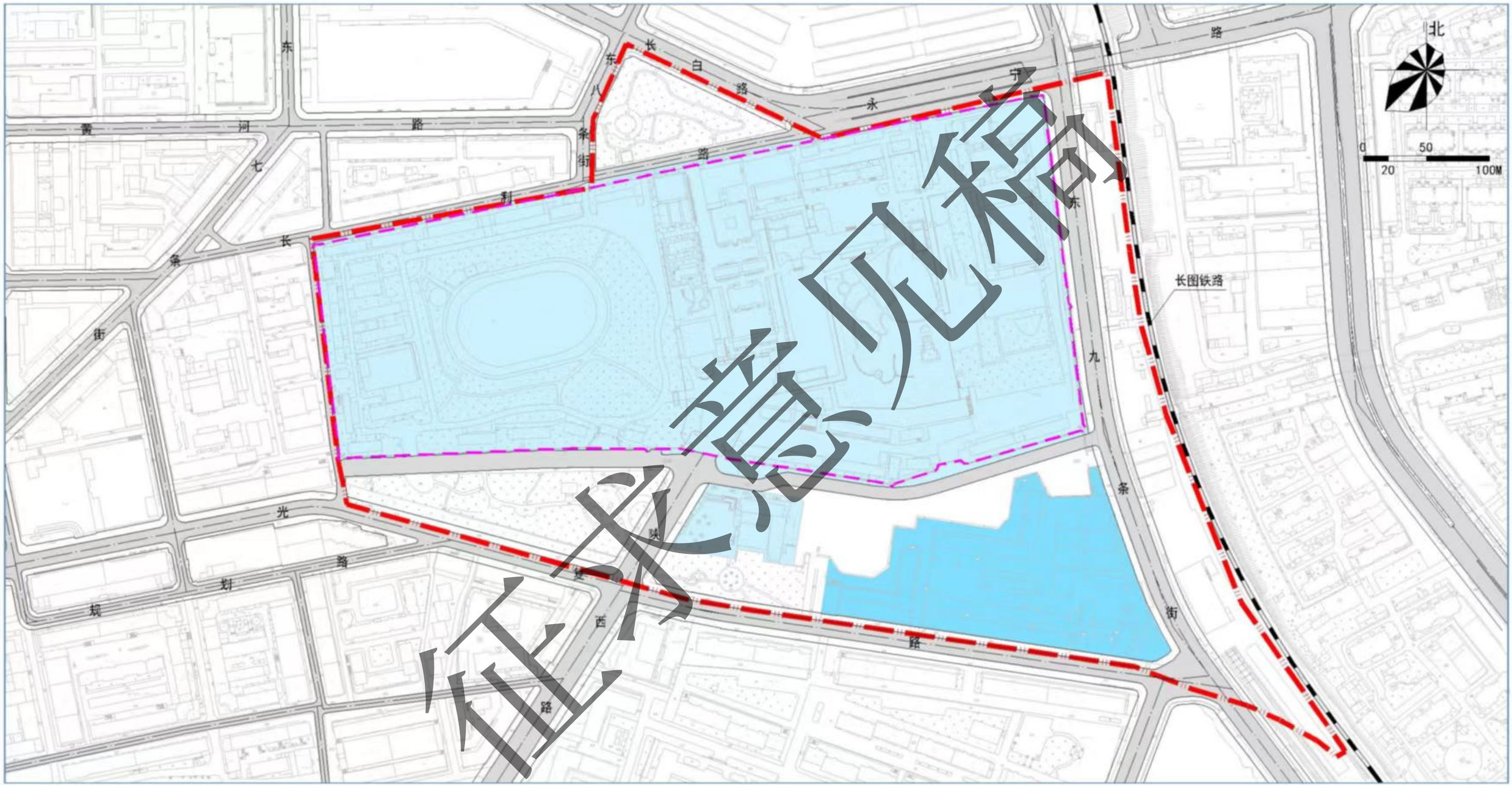

图例

- 历史文化街区界线
- 核心保护区界线
- 规划道路
- 维持建筑原高度不变
- 建筑限高18米

06 建筑高度控制图

MAP OF BUILDING HEIGHT CONTROL

伪满皇宫历史文化街区保护规划（2023-2035年）
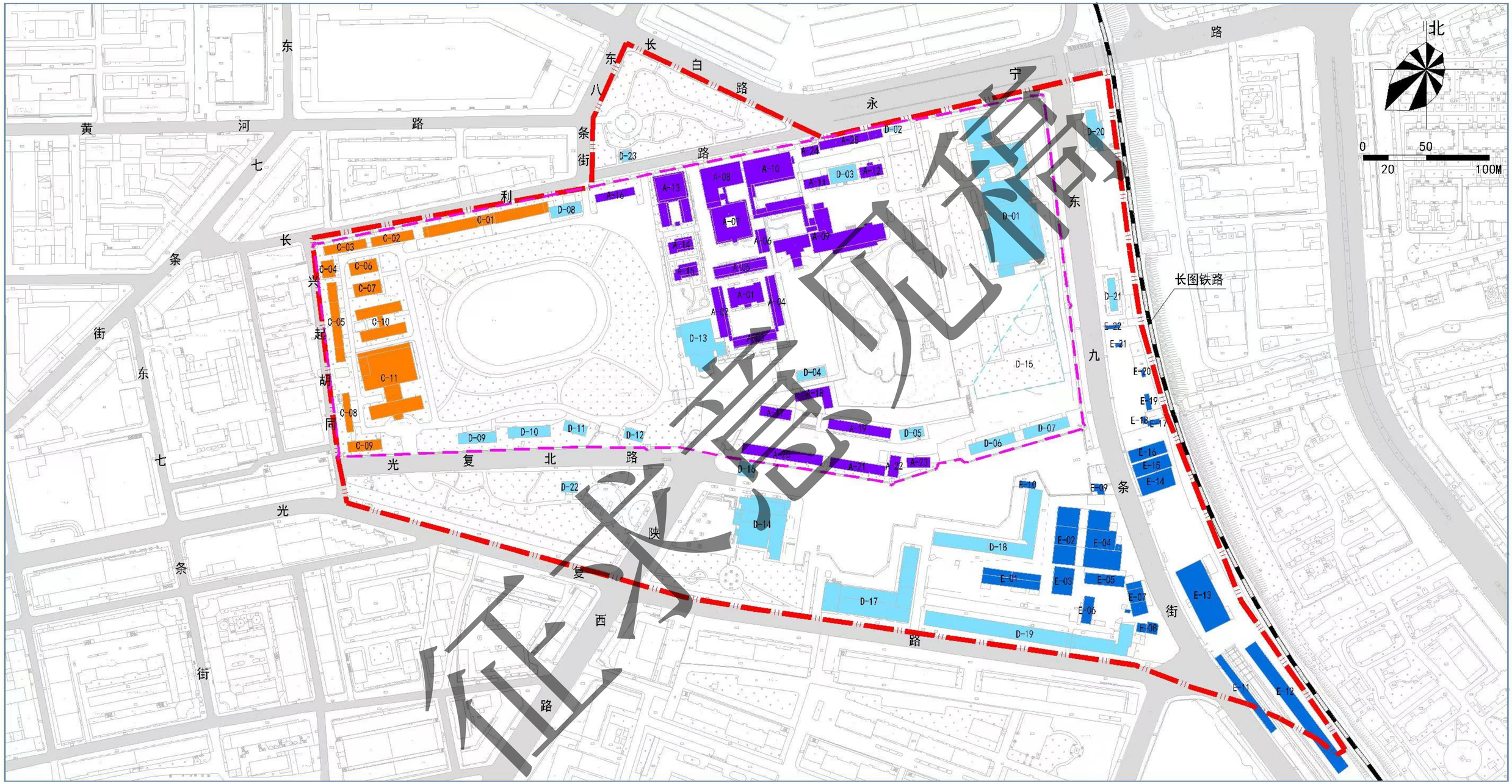
PROTECTION PLANNING OF HISTORICAL AND CULTURAL DISTRICT OF MANCHUKUO IMPERIAL PALACE